PanneauxRoute

Des panneaux de signalisation routière, au format vectoriel .

Version 0.1.3 – 4 mai 2025

Cédric Pierquet
c pierquet – at – outlook . fr
https://forge.apps.education.fr/pierquetcedric/packages-latex

Table des matières

1 Le package PanneauxRoute **2**
1.1 Idée . . . 2
1.2 Historique . . . 2
1.3 Chargement . . . 2
1.4 Commandes et utilisation . . . 2

2 Tableaux récapitulatifs des panneaux disponibles **3**
2.1 Panneaux de Danger . . . 3
2.2 Panneaux de Danger temporaires . . . 5
2.3 Panneaux d'Interdiction et de Priorité . . . 6
2.4 Panneaux d'Interdiction . . . 7
2.5 Panneaux d'Obligation . . . 9
2.6 Panneaux de fin d'Interdiction . . . 10
2.7 Panneaux de fin d'Obligation . . . 11
2.8 Panneaux d'Indication . . . 11
2.9 Panneaux de Signalisation des Services . . . 13
2.10 Panneaux divers . . . 15

3 Aliases, de hauteur 2.5ex **16**



Merci à quark67 pour ses retours.

1 Le package PanneauxRoute

1.1 Idée

L'idée est de proposer des panneaux de signalisation routière pour des documents TEX.

Les panneaux sont au format `pdf`, obtenu à l'aide de fichiers `svg`, donc au format vectoriel, avec comme source :

— https://equipementsdelaroute.cerema.fr/les-signaux-r212.html sous licence etalab 2.0.

1.2 Historique

`v0.1.3` : Nouvelle source et nouvelle licence (etalab 2.0)
`v0.1.2` : Nouveaux panneaux
`v0.1.1` : Ajout du panneau B14 (80, version alternative) pour la limitation de vitesse 80
`v0.1.0` : Version initiale

1.3 Chargement

Le package se charge dans le préambule, via `\usepackage{PanneauxRoute}`, et seul `graphicx` est chargé.

```
\usepackage{PanneauxRoute}
```

1.4 Commandes et utilisation

Chaque panneau (disponible) est disponible au format `pdf` (vectoriel, de fond transparent et provenant de fichiers `svg`) peut-être inséré de deux manières différentes :

— grâce à la commande `\AffPanneau` et le code (officiel) du panneau (voir tableaux) ;
— grâce à une commande *alias*, sous la forme `\pr<NomPanneau>`.

```
\AffPanneau[options graphicx]{<CodePanneau>}
\pr<NomPanneau>[options graphicx]                    %si disponible
```

```
\AffPanneau{A3b} ou \prChausRetG
```

Les deux commandes permettent d'insérer un panneau avec une hauteur de 1.15 cm, mais la taille du panneau peut-être modifiée grâce à un argument optionnel, et entre `[...]`, compatible avec les options de `\includegraphics` (comme `scale`, `height` ou `width`).

Par défaut (dû à `\includegraphics`) les *images* sont placées sur la ligne de base, mais avec `\raisebox` ou `\vcenter`, on peut décaler le panneau verticalement.

```
\raisebox{-0.2\height}{\AffPanneau[height=2ex]{B2b}} donne pareil que
\raisebox{-0.2\height}{\prInterdTournD[height=2ex]}
```

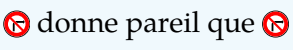

Pour les panneaux de (début/fin de) limitation de vitesse, la commande associée nécessite un argument obligatoire, et entre `{...}`, avec comme possibilités `15/30/50/70/90/110/130` :

```
\prLimVites{30}\prLimVites{50}\prLimVites{70}%
\prLimVites{80}\prLimVites{90}\prLimVites{110}\prLimVites{130}
```

```
\prFinLimVit{30}\prFinLimVit{50}\prFinLimVit{70}%
\prFinLimVit{90}\prFinLimVit{110}
```



2 Tableaux récapitulatifs des panneaux disponibles

2.1 Panneaux de Danger

Type	Panneau	Signification	Alias
A1a		Virage à droite	`\prVirDroit`
A1b		Virage à gauche	`\prVirGauche`
A1c		Succession de virages dont le premier est à droite	`\prVirsDroit`
A1d		Succession de virages dont le premier est à gauche	`\prVirsGauche`
A2a		Cassis ou dos-d'âne	`\prDosAne`
A2b		Ralentisseur de type dos-d'âne	`\prRalDosAne`
A3		Chaussée rétrécie	`\prChausRet`
A3a		Chaussée rétrécie par la droite	`\prChausRetD`
A3b		Chaussée rétrécie par la gauche	`\prChausRetG`
A4		Chaussée particulièrement glissante	`\prChaussGliss`
A6		Pont mobile	`\prPontMob`
A7		Passage à niveau muni de barrières à fonctionnement manuel [...]	`\prPassNiv`
A8		Passage à niveau sans barrières ni demi-barrières	`\prPassNivVap`
A9		Panneau traversée de voies de tramway	`\prPassTram`
A13a		Endroit fréquenté par les enfants	`\prEnfants`
A13b		Passage pour piéton	`\prPietons`
A14		Autres dangers	`\prDanger`
A15a1		Passage d'animaux domestiques	`\prAnimaux`
A15a2		Passage d'animaux domestiques	
A15b		Passage d'animaux sauvages	`\prAnimauxSauv`

Suite page suivante

(Continued)

A15c		Passage de cavaliers	`\prCavaliers`
A16		Descente dangereuse	`\prDescente`
A17		Annonce de feux tricolores	`\prFeux`
A18		Circulation dans les deux sens	`\prDeuxSens`
A19		Risque de chute de pierres ou de présence sur la route [...]	`\prChute`
A20		Débouché sur un quai ou une berge	`\prQuai`
A21		Débouché de cyclistes venant de droite ou de gauche	`\prVelos`
A23		Traversée d'une aire de danger aérien	`\prAvions`
A24		Vent latéral	`\prVent`

2.2 Panneaux de Danger temporaires

Type	Panneau	Signification	Alias
AK2		Dos d'âne ou cassis	`\prDosAneTemp`
AK3		Rétrécissement de chaussée	`\prChausRetTemp`
AK4		Chaussée glissante	`\prChaussGlissTemp`
AK5		Travaux	`\prTravauxTemp`
AK14		Danger	`\prDangerTemp`
AK17		Feux temporaires	`\prFeuxTemp`
AK22		Projection de gravillons	`\prGraviersTemp`
AK30		Embouteillage	`\prBouchonTemp`
AK31		Accident	`\prAccidentTemp`
AK32		Brouillard ou fumées épaisses	`\prBrouillardTemp`

2.3 Panneaux d'Interdiction et de Priorité

Type	Panneau	Signification	Alias
AB1		Intersection où le conducteur est tenu de céder le passage [...]	`\prIntersect`
AB2		Intersection avec une route dont les usagers doivent céder le passage[...]	`\prIntersectPrio`
AB3a		Cédez le passage à l'intersection	`\prCedez`
AB3b		Cédez le passage à l'intersection	`\prCedezInter`
AB4		Arrêt à l'intersection dans les conditions définies [...]	`\prStop`
AB5		Arrêt à l'intersection	`\prArretInter`
AB6		Indication du caractère prioritaire d'une route	`\prRoutePrio`
AB7		Fin du caractère prioritaire d'une route	`\prFinRoutePrio`
AB25		Carrefour à sens giratoire	`\prRondPoint`

2.4 Panneaux d'Interdiction

Type	Panneau	Signification	Alias
B0		Circulation interdite à tout véhicule dans les deux sens	`\prCircInterd`
B1		Sens interdit à tout véhicule	`\prSensInterdit`
B1j		Répétition d'interdiction d'accès à contresens de bretelles [...]	`\prSensInterditJ`
B2a		Interdiction de tourner à gauche à la prochaine intersection	`\prInterdTournG`
B2b		Interdiction de tourner à droite à la prochaine intersection	`\prInterdTournD`
B2c		Interdiction de faire demi-tour sur la route suivie jusqu'à la prochaine intersection	`\prInterdDemiTour`
B3		Interdiction de dépasser tous les véhicules à moteur autres que ceux à deux roues sans side-car	`\prInterdDepass`
B3a		Interdiction aux véhicules automobiles, véhicules articulés, trains doubles ou [...]	`\prInterdVehic`
B4		Arrêt au poste de douane	`\prHalteDouane`
B5a		Arrêt au poste de gendarmerie	`\prHalteGendarm`
B5b		Arrêt au poste de police	`\prHaltePolice`
B5c		Arrêt au poste de péage	`\prHaltePeage`
B6a1		Stationnement interdit	`\prStationInterd`
B6a2		Stationnement interdit du 1er au 15 du mois	`\prStationInterdQA`
B6a3		Stationnement interdit du 16 à la fin du mois	`\prStationInterdQB`
B6d		Arrêt et stationnement interdits	`\prArStatInterd`
B7a		Accès interdit aux véhicules à moteur à l'exception des cyclomoteurs	`\prInterdMotSaufCyc`
B7b		Accès interdit à tous les véhicules à moteur	`\prInterdMot`
B8		Accès interdit aux véhicules affectés au transport de marchandises	`\prInterdMarchand`
B9a		Accès interdit aux piétons	`\prInterdPietons`

Suite page suivante

(Continued)

B9b		Accès interdit aux cycles	`\prInterdCycles`
B9c		Accès interdit aux véhicules à traction animale	`\prInterdTracAnim`
B9d		Accès interdit aux véhicules agricoles à moteur	`\prInterdAgricMot`
B9e		Accès interdit aux voitures à bras à l'exclusion de celles visées [...]	`\prInterdBras`
B9f		Accès interdit aux véhicules de transport en commun de personnes	`\prInterdTranspComm`
B9g		Accès interdit aux cyclomoteurs	`\prInterdCyclomot`
B9h		Accès interdit aux motocyclettes et motocyclettes légères [...]	`\prInterdCycloMoto`
B9i		Accès interdit aux véhicules tractant une caravane ou une remorque de plus de 250 kg [...]	`\prInterdCaravanes`
B10a		Accès interdit aux véhicules, véhicules articulés, trains doubles [...]	`\prInterdLong`
B11		Accès interdit aux véhicules dont la largeur, chargement compris, est supérieure [...]	`\prInterdLarg`
B12		Accès interdit aux véhicules dont la hauteur, chargement compris, est supérieure [...]	`\prInterdHaut`
B13		Accès interdit aux véhicules, véhicules articulés, trains doubles ou ensemble de véhicules [...]	`\prInterdPoids`
B13a		Accès interdit aux véhicules pesant sur un essieu plus que le nombre indiqué	`\prInterdPoidsEssieu`
B14_x	Limite de vitesse		`\prLimVites{x}`
B15		Cédez le passage à la circulation venant en sens inverse	`\prCedezInv`
B16		Signaux sonores interdits	`\prInterdSons`
B17		Interdiction aux véhicules de circuler sans maintenir entre eux un intervalle [...]	`\prDistance`
B18a		Accès interdit aux véhicules transportant des marchandises explosives ou facilement [...]	`\prExplos`
B18b		Accès interdit aux véhicules transportant des marchandises susceptibles de polluer les eaux [...]	`\prPollu`
B18c		Accès interdit aux véhicules transportant des marchandises dangereuses définies par l'arrêté [...]	`\prDangereuses`
B19		Autres interdictions dont la nature est indiquée par une inscription sur le panneau	

2.5 Panneaux d'Obligation

Type	Panneau	Signification	Alias
B21-1		Obligation de tourner à droite avant le panneau	`\prObliAvDroite`
B21-2		Obligation de tourner à gauche avant le panneau	`\prObliAvGauche`
B21a1		Contournement obligatoire par la droite	`\prContournDroite`
B21a2		Contournement obligatoire par la gauche	`\prContournGauche`
B21b		Direction obligatoire à la prochaine intersection : tout droit	`\prToutDroit`
B21c1		Direction obligatoire à la prochaine intersection : à droite	`\prObliDroite`
B21c2		Direction obligatoire à la prochaine intersection : à gauche	`\prObliGauche`
B21d1		Directions obligatoires à la prochaine intersection : tout droit ou à droite	`\prObliToutDroite`
B21d2		Directions obligatoires à la prochaine intersection : tout droit ou à gauche	`\prObliToutGauche`
B21e		Directions obligatoires à la prochaine intersection : à droite ou à gauche	`\prObliDroiteGauche`
B22a		Piste ou bande obligatoire pour les cycles sans side-car	`\prObliCycles`
B22b		Chemin obligatoire pour piétons	`\prObliPietons`
B22c		Chemin obligatoire pour cavaliers	`\prObliCavaliers`
B25		Vitesse minimale obligatoire	`\prObliVitesse`
B26		Chaînes à neige obligatoires sur au moins deux roues motrices	`\prObliChaines`
B27a		Voie réservée aux véhicules routiers de transports en commun des lignes régulières dûment […]	`\prObliBus`
B27b		Voie réservée aux tramways	`\prObliTrams`
B29		Autres obligations dont la nature est mentionnée par une inscription sur le panneau	

2.6 Panneaux de fin d'Interdiction

Type	Panneau	Signification	Alias
B31		Fin de toutes les interdictions précédemment signalées[…]	`\prFinInterd`
B33_x	Fin de Limite de vitesse		`\prFinLimVit{x}`
B34		Fin d'interdiction de dépasser notifiée par le panneau B3	`\prFinIntDepass`
B34a		Fin d'interdiction de dépasser notifiée par le panneau B3a	`\prFinIntDepassCam`
B35		Fin d'interdiction de l'usage de l'avertisseur sonore	`\prFinIntSons`
B39		Fin d'interdiction dont la nature est indiquée sur le panneau	

2.7 Panneaux de fin d'Obligation

Type	Panneau	Signification	Alias
B40		Fin de piste ou bande obligatoire pour cycles	`\prFinPisteOblCycl`
B41		Fin de chemin obligatoire pour piétons	`\prFinChemPiet`
B42		Fin de chemin obligatoire pour cavaliers	`\prFinChemCav`
B43		Fin de vitesse minimale obligatoire	`\prFinVitObli`
B44		Fin d'obligation de l'usage des chaînes à neige	`\prFinChaines`
B45a		Fin de voie réservée aux véhicules routiers de transports en commun des lignes régulières [...]	`\prFinVoieBus`
B49		Fin d'obligation dont la nature est mentionnée par une inscription sur le panneau	

2.8 Panneaux d'Indication

Type	Panneau	Signification	Alias
C1a		Lieu aménagé pour le stationnement	`\prParking`
C1b		Lieu aménagé pour le stationnement gratuit à durée limitée avec contrôle par un disque	`\prParkDisq`
C1c		Lieu aménagé pour le stationnement payant	`\prParkPay`
C3		Risque d'incendie	`\prIncendie`
C44		Vitesse conseillée	`\prVitConseil`
C4b		Fin de vitesse conseillée	`\prFinVitConseil`
C5		Station de taxis	`\prTaxis`
C6		Arrêt d'autobus	`\prArretBus`
C8		Emplacement d'arrêt d'urgence	`\prArretUrg`
C12		Circulation à sens unique	`\prCircSensUniq`
C13a		Impasse	`\prImpasse`

Suite page suivante

(Continued)

C13b		Présignalisation d'une impasse	`\prPreImpasse`
C18		Priorité par rapport à la circulation venant en sens inverse	`\prPriorSensInv`
C20a		Passage pour piétons	`\prPassPietons`
C20c		Traversée de voies de tramways	`\prTravTrams`
C23		Stationnement réglementé pour les caravanes et les autocaravanes	`\prStatCarav`
C24a1		Voies affectées	`\prVoiesAffA`
C24a4		Voies affectées	`\prVoiesAffB`
C24b1		Voies affectées	`\prVoiesAffC`
C24b2		Voies affectées	`\prVoiesAffD`
C24c1		Voies affectées	`\prVoiesAffE`
C24c2		Voies affectées	`\prVoiesAffF`
C25a		Indication aux frontières des limites de vitesse sur le territoire français	`\prVitFront`
C25b		Rappel des limites de vitesse sur autoroute	`\prVitAutor`
C26a		Voie de détresse à droite	`\prDetresseD`
C26b		Voie de détresse à gauche	`\prDetresseG`
C27		Surélévation de chaussée	`\prChausseSur`
C28a		Réduction du nombre de voies sur une route à chaussées séparées ou sur un créneau [...]	`\prReducVoieA`
C28b		Réduction du nombre de voies sur une route à chaussées séparées ou sur un créneau [...]	`\prReducVoieB`
C29b		Créneau de dépassement à trois voies affectées "deux voies dans un sens et une voie dans l'autre"	`\prCreneauDepas`
C30		Fin d'un créneau de dépassement à trois voies affectées	`\prFinCreneauDepas`
C50		Indications diverses	
C62		Présignalisation d'une borne de retrait de ticket de péage	`\prTickPeage`

Suite page suivante

(Continued)

C64a		Paiement auprès d'un péagiste	`\prPaiemPeage`
C64b		Paiement automatique par CB	`\prPaiemCB`
C64c		Paiement automatique par pièces de monnaie	`\prPaiemPieces`
C64d1		Paiement automatique par pièces et billets	`\prPaiemPiecBil`
C64d2		Paiement automatique par Télépéage	`\prPaiemTelepeage`
C107		Route à accès réglementé	`\prRouteRegl`
C108		Fin de route à accès réglementé	`\prFinRouteRegl`
C111		Entrée d'un tunnel	`\prEntrTunnel`
C112		Sortie de tunnel	`\prSortieTunnel`
C113		Piste ou bande cyclable conseillée et réservée aux cycles à deux ou trois roues	`\prPisteCycl`
C114		Fin d'une piste ou d'une bande cyclable conseillée et réservée aux cycles à deux ou trois	`\prFinPisteCycl`
C115		Voie verte	`\prVoieVerte`
C116		Fin de voie verte	`\prFinVoieVerte`
C207		Début d'une section d'autoroute	`\prDebAutor`
C208		Fin d'une section d'autoroute	`\prFinAutor`

2.9 Panneaux de Signalisation des Services

Type	Panneau	Signification	Alias
CE1		Poste de secours	`\prPosteSecours`
CE2a		Poste d'appel d'urgence	`\prPosteSecUrg`
CE2b		Cabine téléphonique publique	`\prCabineTel`
CE3a		Informations relatives aux services ou activités touristiques	`\prInfos`

Suite page suivante

(Continued)

CE4a		Terrain de camping pour tentes	`\prCampingT`
CE4b		Terrain de camping pour caravanes et autocaravanes	`\prCampingC`
CE4c		Terrain de camping pour tentes, caravanes et autocaravanes	`\prCampingTC`
CE5a		Auberge de jeunesse	`\prAubergJeun`
CE5b		Chambre d'hôtes ou gîte	`\prGite`
CE6a		Point de départ d'un itinéraire pédestre	`\prItinPedest`
CE6b		Point de départ d'un circuit de ski de fond	`\prItinSkiFond`
CE7		Emplacement pour pique-nique	`\prPicNic`
CE8		Gare auto / train	`\prGareAutoTrain`
CE9		Parc de stationnement sous vidéoprotection	`\prParkVideo`
CE10		Embarcadère	`\prEmbarcad`
CE12		Toilettes ouvertes au public	`\prToilettes`
CE14		Installations accessibles aux personnes handicapées à mobilité réduite	`\prAccesHandic`
CE15a		Poste de distribution de carburant ouvert 7 jours sur 7 et 24 heures sur 24	`\prEssence`
CE15c		Poste de distribution de carburant ouvert 7 jours sur 7 et 24 heures sur 24 [...]	`\prEssenceGPL`
CE16		Restaurant ouvert 7 jours sur 7	`\prRestau`
CE17		Hôtel ou motel ouvert 7 jours sur 7	`\prHotel`
CE18		Débit de boissons ou établissement proposant des collations sommaires ouvert 7 jours sur 7	`\prBoissons`
CE19		Emplacement de mise à l'eau d'embarcations légères	`\prEmbarcLeg`
CE20a		Gare de téléphérique	`\prTelepher`
CE20b		Point de départ d'un télésiège ou d'une télécabine	`\prTelecabin`
CE21		Point de vue	`\prPointVue`

Suite page suivante

(Continued)

CE22		Fréquence d'émission d'une station de radiodiffusion dédiée aux informations [...]	`\prRadio`
CE23		Jeux d'enfants	`\prJeuxEnfants`
CE24		Station de vidange pour caravanes, auto-caravanes et cars	`\prVidange`
CE25		Distributeur de billets de banque	`\prDistribBill`
CE26		Station de gonflage, hors station service, dont l'usage est gratuit	`\prGonflage`
CE27		Point de détente	`\prDetente`
CE28		Poste de dépannage	`\prPosteDepann`
CE29		Moyen de lutte contre l'incendie	`\prLutteIncendie`
CE30a		Issue de secours vers la droite	`\prIssueSecD`
CE30b		Issue de secours vers la gauche	`\prIssueSecG`
CE50		Installations ou services divers	

2.10 Panneaux divers

: B50a

: B50b

: B50c

: B50d

: B50e

: B51_30

: B53

: B55

: B57

: B59

: B49VL

 : C24a

3 Aliases, de hauteur 2.5ex

: \prVirDroit
: \prVirGauche
: \prVirsDroit
: \prVirsGauche
: \prDosAne
: \prRalDosAne
: \prChausRet
: \prChausRetD
: \prChausRetG
: \prChaussGliss

: \prPontMob
: \prPassNiv
: \prPassNivVap
: \prPassTram
: \prEnfants
: \prPietons
: \prDanger
: \prAnimaux
: \prAnimauxSauv
: \prCavaliers

: \prDescente
: \prFeux
: \prDeuxSens
: \prChute
: \prQuai
: \prVelos
: \prAvions
: \prVent

: \prDosAneTemp
: \prIntersectPrio
: \prChaussGlissTemp
: \prTravauxTemp

: \prDangerTemp
: \prFeuxTemp
: \prGraviersTemp
: \prBouchonTemp

: \prAccidentTemp
: \prBrouillardTemp

: \prIntersect
: \prIntersectPrio
: \prCedez

: \prCedezInter
: \prStop
: \prArretInter

: \prRoutePrio
: \prFinRoutePrio
: \prRondPoint

: \prCircInterd
: \prSensInterdit
: \prInterdTournG
: \prInterdTournD
: \prInterdDemiTour
: \prInterdVehic
: \prHalteDouane
: \prHalteGendarm
: \prHaltePolice
: \prHaltePeage
: \prStationInterd
: \prStationInterdQA
: \prStationInterdQB
: \prArStatInterd
: \prInterdMotSaufCyc
: \prInterdMot
: \prInterdMarchand
: \prInterdPietons
: \prInterdCycles
: \prInterdTracAnim
: \prInterdAgricMot

: \prInterdBras
: \prInterdTranspComm
: \prInterdCyclomot
: \prInterdCycloMoto
: \prInterdCaravanes
: \prInterdLong
: \prInterdLarg
: \prInterdHaut
: \prInterdPoids
: \prInterdPoidsEssieu
: \prLimVites{15}
: \prLimVites{30}
: \prLimVites{50}
: \prLimVites{70}
: \prLimVites{80}
: \prLimVites{90}
: \prLimVites{110}
: \prLimVites{130}
: \prCedezInv
: \prInterdSons
: \prDistance

: \prExplos
: \prPollu
: \prDangereuses
: \prObliDroite
: \prObliGauche
: \prContournDroite
: \prContournGauche
: \prToutDroit
: \prObliDroite
: \prObliGauche
: \prObliToutDroite
: \prObliToutGauche
: \prObliDroiteGauche
: \prObliCycles
: \prObliPietons
: \prObliCavaliers
: \prObliVitesse
: \prObliChaines
: \prObliBus
: \prObliTrams

: \prFinInterd
: \prFinLimVit{15}
: \prFinLimVit{30}
: \prFinLimVit{50}

: \prFinLimVit{70}
: \prFinLimVit{90}
: \prFinLimVit{110}
: \prFinLimVit{130}

: \prFinIntDepass
: \prFinIntDepassCam
: \prFinIntSons

: \prFinPisteCycl
: \prFinChemPiet

: \prFinChemCav
: \prFinVitObli

: \prFinChaines
: \prFinVoieBus

: \prParking
: \prParkDisq
: \prParkPay
: \prIncendie

: \prVitConseil
: \prFinVitConseil
: \prTaxis
: \prArretBus

: \prArretUrg
: \prCircSensUniq
: \prImpasse
: \prPreImpasse

: \\prPriorSensInv
: \prPassPietons
: \prTravTrams
: \prStatCarav
: \prVoiesAffA
: \prVoiesAffB
: \prVoiesAffC

: \prPaiemPeage
: \prPaiemCB
: \prPaiemPieces
: \prPaiemPiecBil
: \prPaiemTelepeage

: \prPosteSecours
: \prPosteSecUrg
: \prCabineTel
: \prInfos
: \prCampingT
: \prCampingC
: \prCampingTC
: \prAubergJeun
: \prGite
: \prItinPedest
: \prItinSkiFond
: \prPicNic

: \prVoiesAffD
: \prVoiesAffE
: \prVoiesAffF
: \prVitFront
: \prVitAutor
: \prDetresseD
: \prDetresseG

: \prRouteRegl
: \prFinRouteRegl
: \prEntrTunnel
: \prSortieTunnel
: \prPisteCycl

: \prGareAutoTrain
: \prParkVideo
: \prEmbarcad
: \prToilettes
: \prAccesHandic
: \prEssence
: \prEssenceGPL
: \prRestau
: \prHotel
: \prBoissons
: \prEmbarcLeg
: \prTelepher

: \prChausseSur
: \prReducVoieA
: \prReducVoieB
: \prCreneauDepas
: \prFinCreneauDepas

: \prFinPisteCycl
: \prVoieVerte
: \prFinVoieVerte
: \prDebAutor
: \prFinAutor

: \prTelecabin
: \prPointVue
: \prRadio
: \prJeuxEnfants
: \prVidange
: \prDistribBill
: \prGonflage
: \prDetente
: \prPosteDepann
: \prLutteIncendie
: \prIssueSecD
: \prIssueSecG